Tablero de Delitos
Ciudad de Buenos Aires

CODER HOUSE

Buenos Aires Presente

Pagina 1 / Portada

Pagina 2 / Brief

Pagina 3 / Analisis Temporal

Pagina 3 / Analisis de Desncidad

Pagina 3 / Analisis Fraja Horaria

Pagina 4 / Concluciones

Pagina 5 / Certificado

Gonzalo Cueto Escalante

Brief

Objetivo del proyecto

Este Dashboard está diseñado con el fin de informar y concientizar a los habitantes de la Ciudad Autónoma de Buenos Aires sobre la situación de seguridad en su entorno. El objetivo específico es proporcionar datos claros para identificar: Las zonas más vulnerables (Comunas/Barrios) en términos de incidencia delictiva. Los patrones temporales (horarios) de mayor riesgo. Los tipos de delitos predominantes en distintos puntos geográficos. La ubicación de las Comisarías encargadas de la seguridad de cada zona, promoviendo la cercanía y la acción ciudadana.

Info general del proyecto

Titulo : CABA Segura: Análisis de Riesgo Geográfico y Delictivo

Organizacion : Gonzalo Cueto

Fecha : 17/10/2025

ETL/Modelado: Microsoft Excel (Power Query)
Visualización/Dashboard: Looker Studio (antes Google Data Studio)
Diseño/Paleta: PaletColors

Fuente de Datos : Datos Abiertos de la Ciudad de Buenos Aires (principalmente Seguridad y Geografía): https://data.buenosaires.gob.ar/dataset/

Estructura

Página 1 : Menú Principal Título, descripción concisa del objetivo, botones de navegación hacia las otras páginas. Página 2 : Brief & Metodología Este documento (el Brief), explicación de las fuentes de datos y la metodología de cálculo (ej. cómo se calculan las tasas, la advertencia sobre la relación Comisaría-Comuna).
Página 3 : Análisis Geográfico y Temporal (Gráficos) Todos los gráficos y mapas interactivos con filtros de tiempo y geografía. Página 4 : Conclusiones y Respuestas Resumen de los hallazgos principales, respuestas directas a las preguntas clave del análisis y conclusiones sobre tendencias.

Publico

- Habitantes de la CABA (Ciudadanos, vecinos, estudiantes).
- Autoridades locales y personal de seguridad (para toma de decisiones rápidas).
- Analistas e Investigadores interesados en seguridad urbana.

Hipotesis :

1. ¿Cómo ha evolucionado el número total de delitos mes a mes a lo largo del período de tiempo capturado?

2. ¿Cuál es el Top 5 de tipos de delito más frecuentes en la Ciudad?

3. ¿Existe una tendencia estacional en la ocurrencia de delitos (ej. más delitos en verano o invierno)?

4. ¿Cuál es el promedio semanal/diario de delitos por tipo?

5. ¿Ha habido algún cambio significativo en la proporción de tipos de delitos (ej. Robos vs. Hurtos) a lo largo de los años?

6. ¿Cuál es la Comuna con la mayor tasa de delitos (o la mayor cantidad total de delitos)?

7. ¿Qué Comisaría tiene la mayor carga de trabajo (más denuncias) y en qué Comuna se ubica?

8. ¿Cuál es la Comuna más segura (la de menor tasa/cantidad de delitos)?

9. ¿Cómo se distribuyen geográficamente los Robos vs. los Hurtos en el mapa de la Ciudad?

10. ¿Cuáles son los tipos de delito predominantes en cada una de las Comunas clave?

11. ¿Cuáles son los delitos menos comunes y en qué áreas se concentran?

12. ¿Cuál es el radio de cobertura promedio de una Comisaría, analizado por la cantidad de barrios que abarca?

13. ¿Qué patrones de delitos se observan en las Comunas con alta densidad poblacional vs. baja densidad?

14. ¿Cómo se comparan los indicadores de seguridad entre Comunas vecinas (ej. Comuna 14 vs. Comuna 13)?

15. Si elijo la Comuna X, ¿cuál es la Comisaría con más casos y cuál es el tipo de delito más denunciado en esa Comisaría?

Graficos :

- Mapa de Coropletas (Geográfico) Distribución de delitos por Comuna. Usar escala de color (Amarillo/Rojo) para indicar el riesgo.

- Gráfico de Líneas Tendencia histórica y estacional de los delitos.

- Gráfico de Barras Top 5 de tipos de delitos y Ranking de Comunas por cantidad.

- Gráfico Circular / de Anillo Distribución porcentual de los tipos de delito.

- Tabla de Indicadores (Scorecard) Indicadores clave: Total de Delitos, Tasa de Delito (si se integra población).

- Mapa de Puntos Ubicación exacta de las Comisarías (para la dimensión geográfica de apoyo).

Tipos de delitos mas frecuentes y evolucion en el tiempo

Tipo de Delito

1 ene 2024 - 25 mar 2

Buenos Aires Presente

Total de tipos de delitos por año

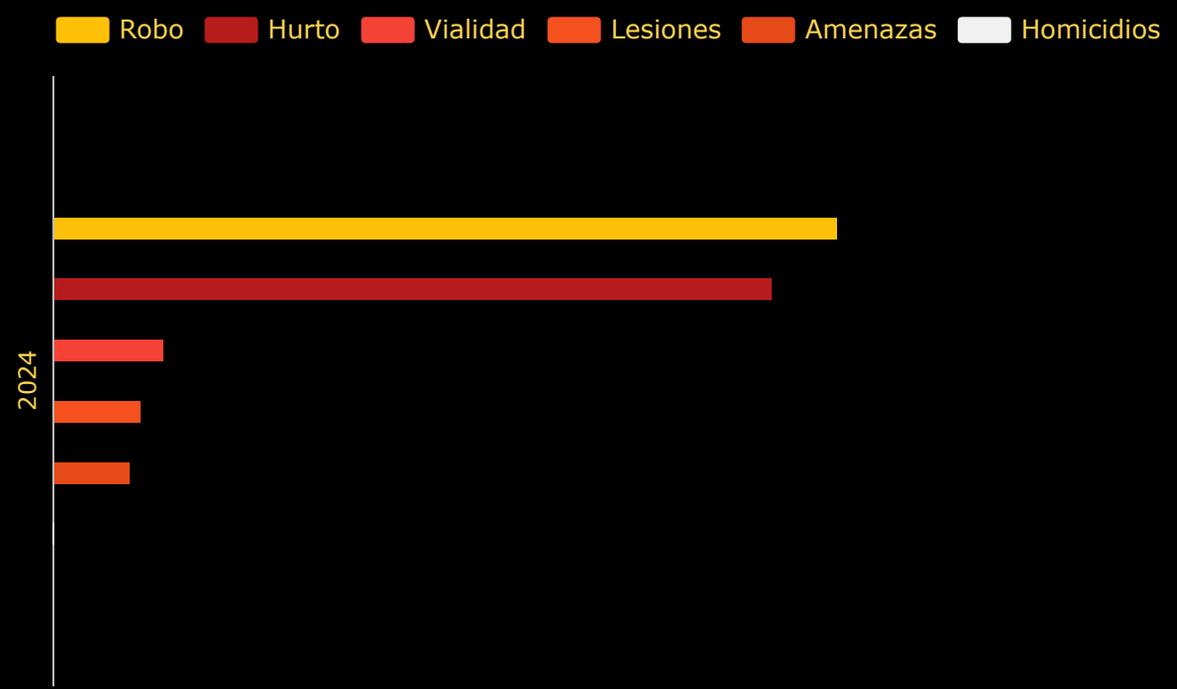

Meses con mas frecuencia de delitos

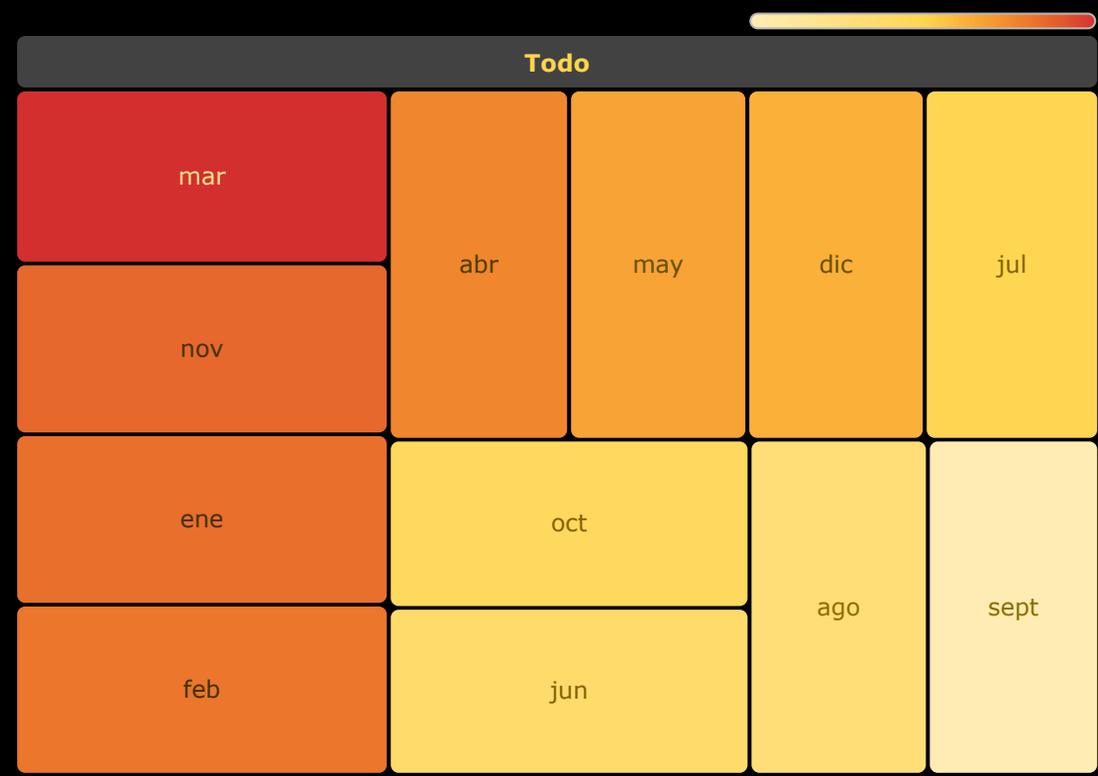

Numero de delitos en los distintos años por mes

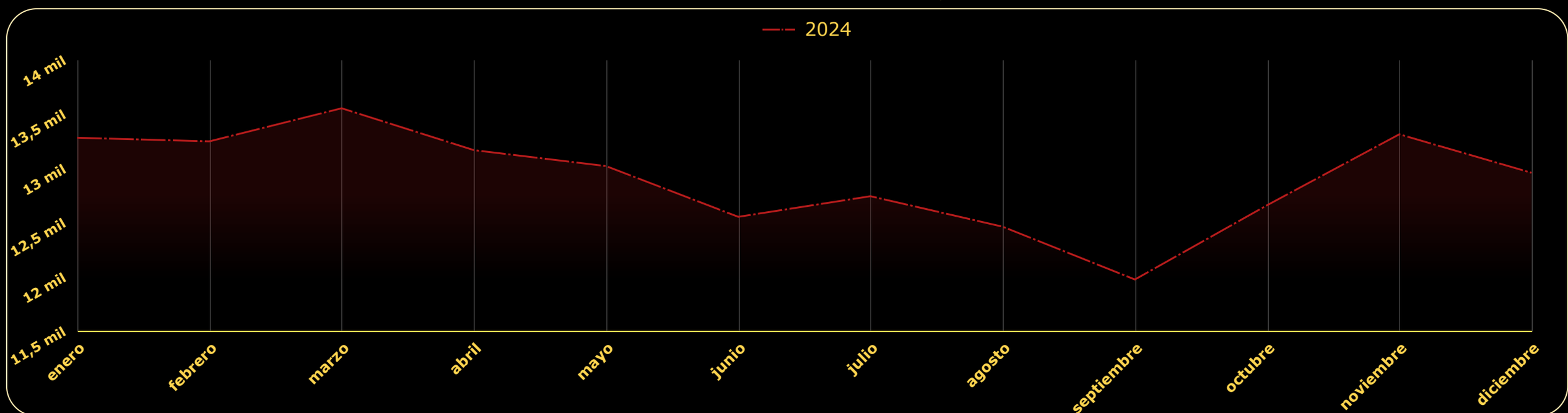

Distribucion de los delitos y puntos de soporte

Total de delitos

barrio

dia

Delitos con arma

Cantidad de delitos por barrio

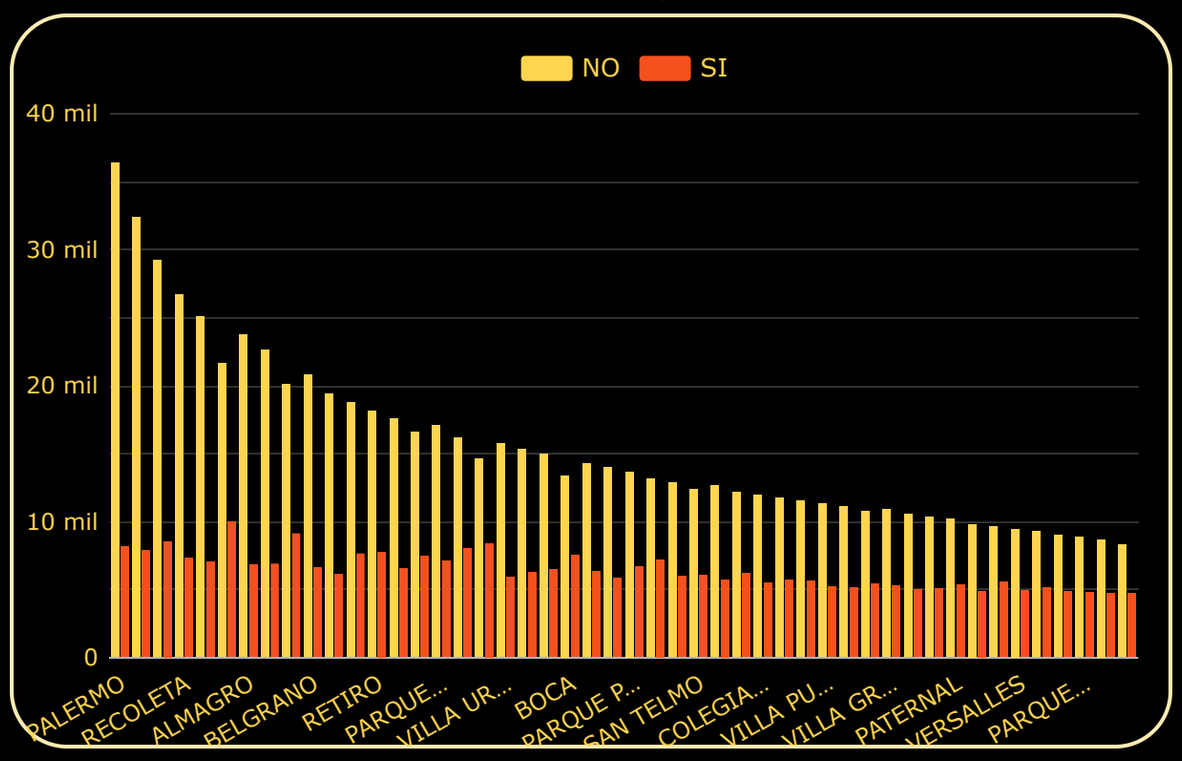

Densidad de Delitos por zona

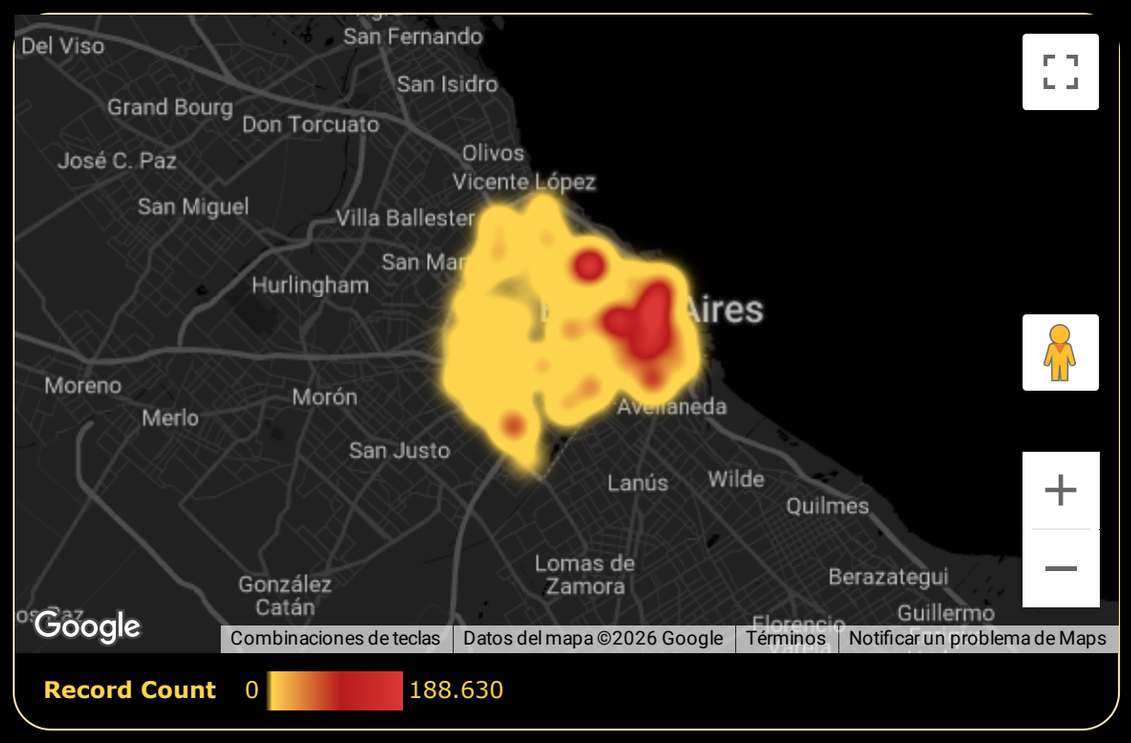

Dias donde se frecuentan mas delitos

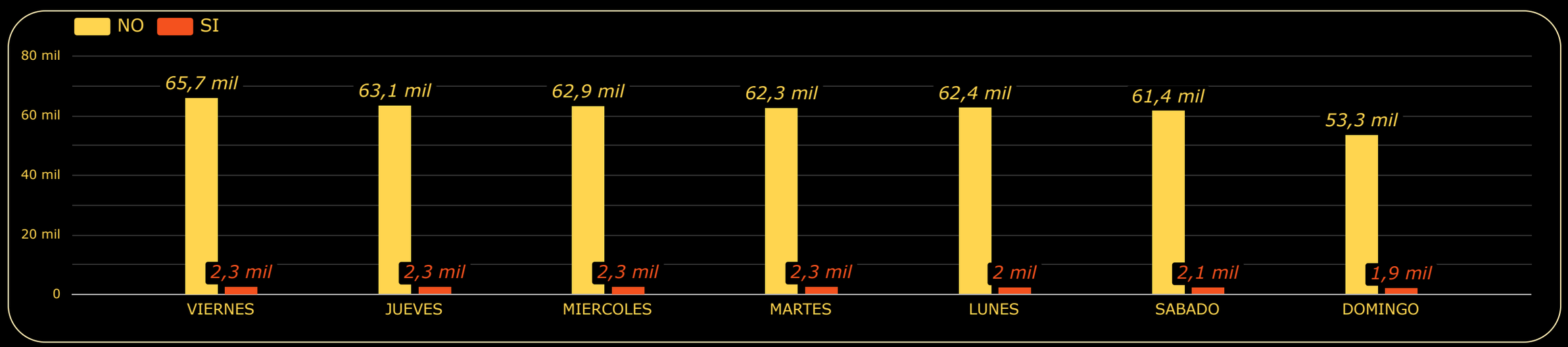

Comisarias

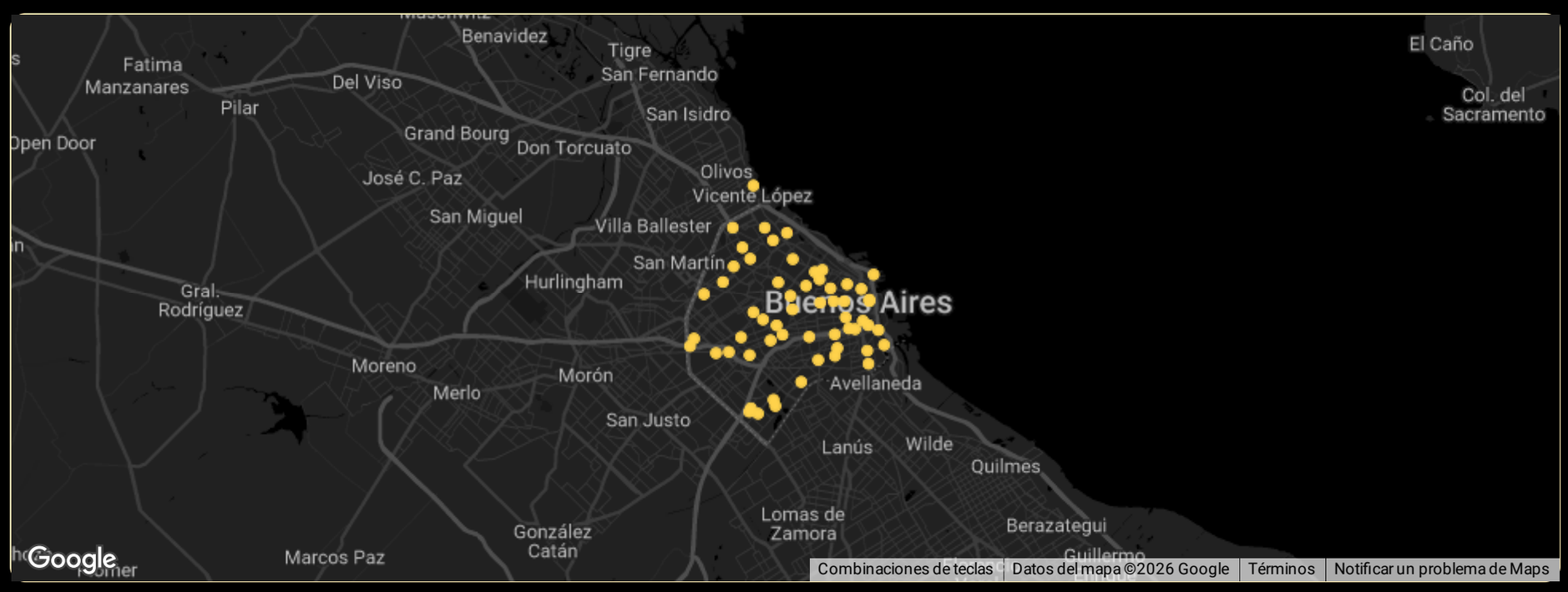

Análisis Franjas Horarias

franja_horaria

0 23

dia

Selecciona un periodo

Cantidad de delitos por tipo

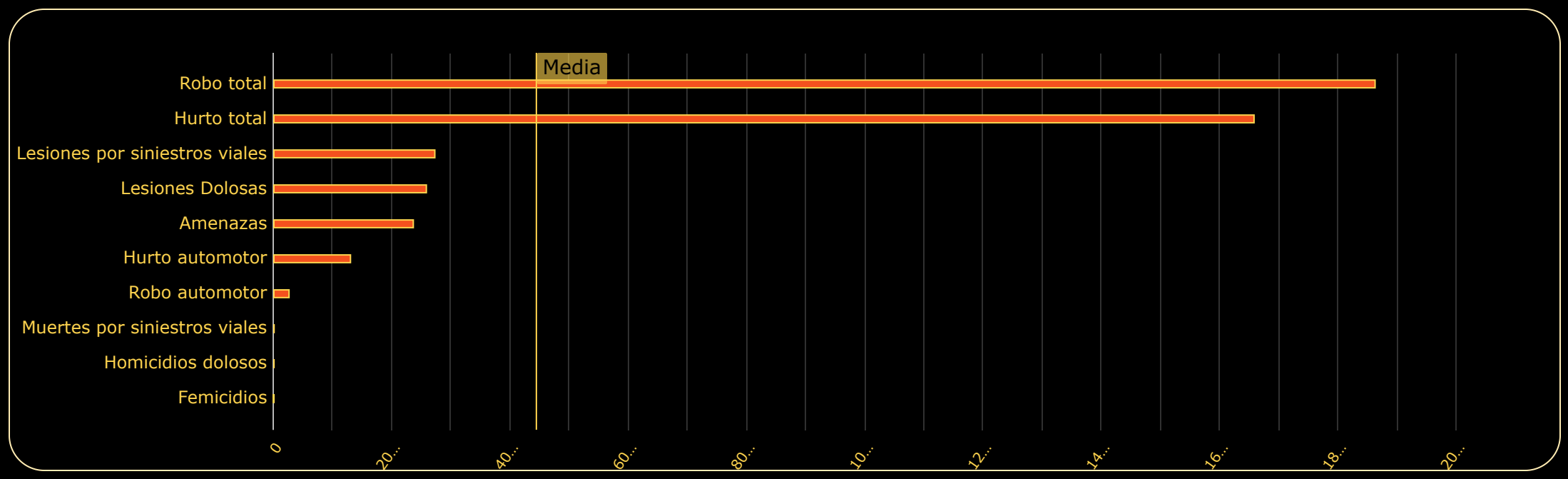

Porcentaje de delitos por categoria

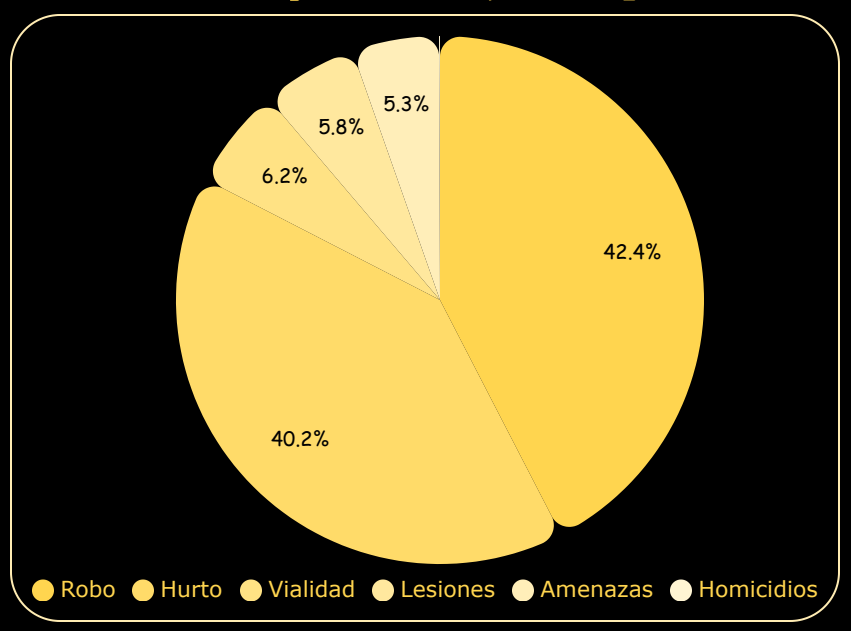

Momentos mas inseguros

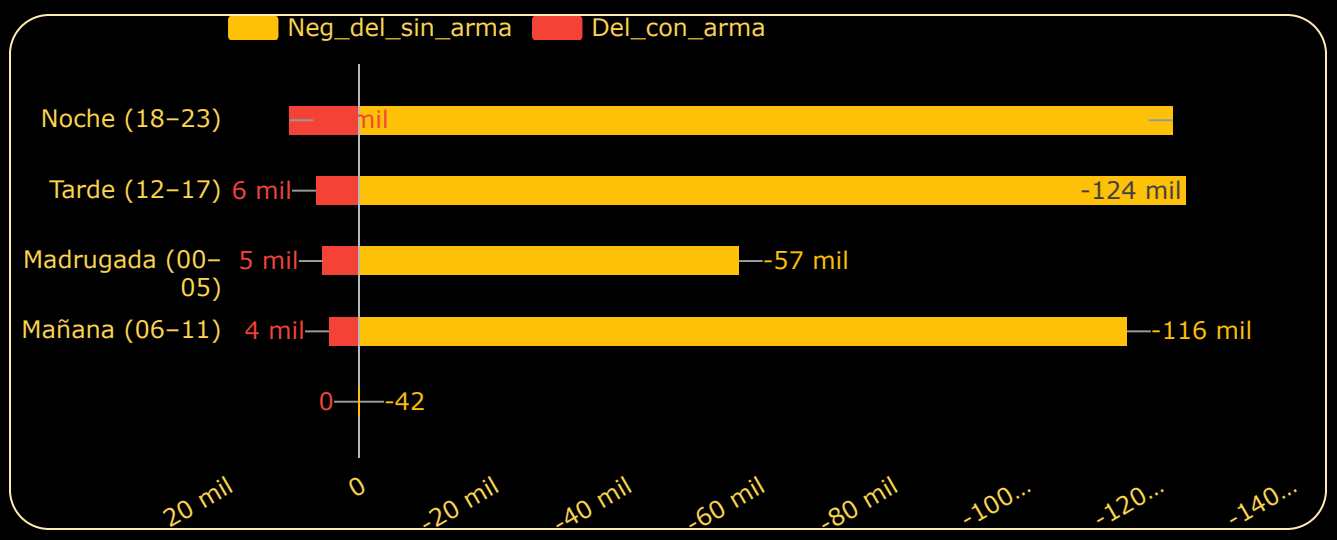

Evolución de los Delitos a lo Largo del Día

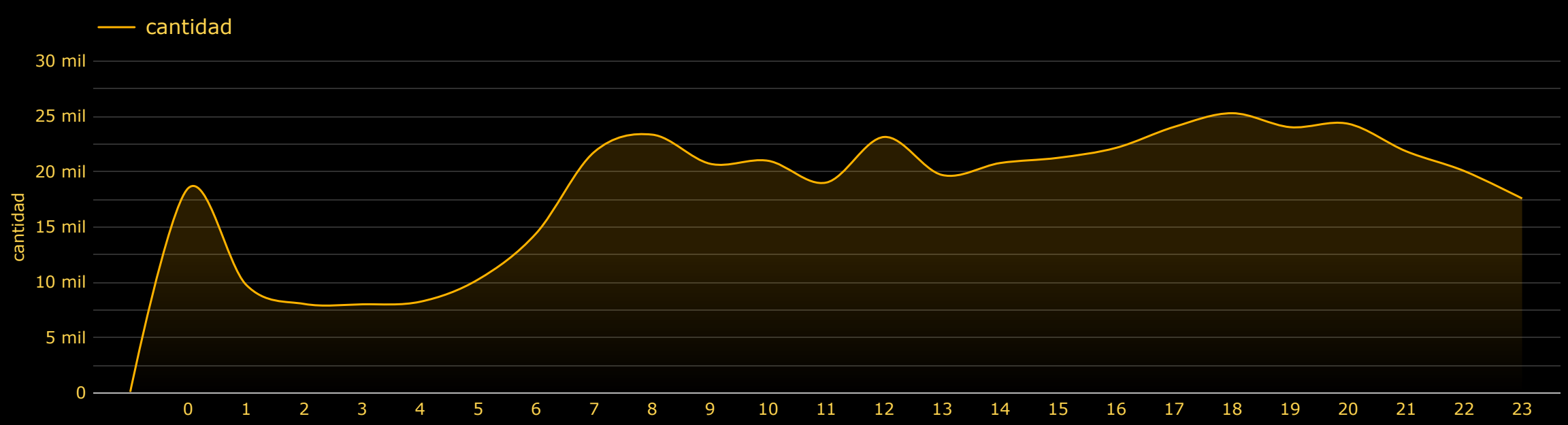

Certificacion Google Analytics

GOOGLE ANALYTICS
CERTIFIED

This acknowledges that

Gonza Cueto

Has successfully completed and is certified in

Google Analytics Certification

Issue Date: November 3, 2025
Expiry Date: November 3, 2026
Certificate ID: 165448771